S-2021-2036 16/11/2021 14:09:40

EMASA
Empresa Municipal
Aguas de Málaga
Plaza General Torrijos, 2
Edif. Hospital Noble 29006 Málaga
900 777 420 LLAMADA GRATUITA

DOC MALAGA SITECO PHASE 2 SL.

D. Alexandre Gamboa Abreu Pessegueiro

Avenida de la Aurora nº 55, Entreplanta
29.001 Málaga

N/Ref.: JCTM/igr
E-2021-4880
Expte.: 2021/081

Málaga, 16 de noviembre de 2021

ASUNTO: SOLICITUD SUFICIENCIA INFRAESTRUCTURAS DE SANEAMIENTO Y AGUA POTABLE PARA EL SUNC.BM-4 (a+b) "Ampliación de Plaza Mayor y del DOC 2ª Fase"

Estimado cliente:

En contestación a su e-mail referenciado, en base a su solicitud de suficiencia de infraestructuras de saneamiento y agua potable para el SUNC.BM-4 (a+b) "Ampliación de Plaza Mayor y del DOC 2ª Fase", les informamos lo siguiente:

REDES E INSTALACIONES DE AGUA POTABLE

El nuevo de tramo de red FD-200 que van ejecutan por el vial sur (calle Teresa Carreño) han de conectarlo a la red FD-300 gestionada por EMASA, y no a la red privada de Plaza Mayor. Si se estima oportuno, y siempre a petición de Bomberos, se puede trasladar el hidrante existente en la glorieta de Alfonso Ponce de León al punto indicado en el plano adjunto.

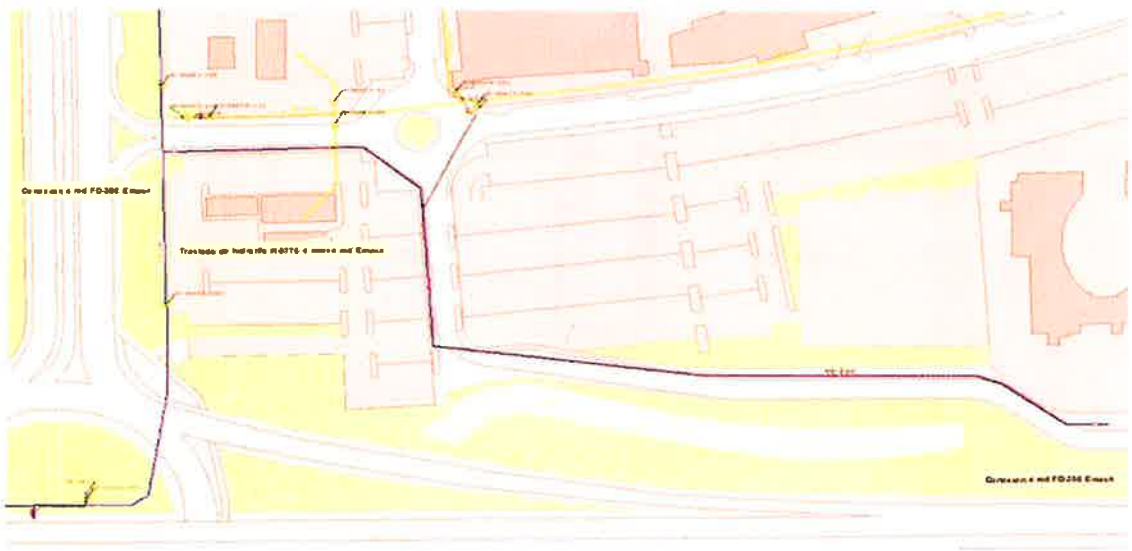

CSV: 07418d05-9813-4ed9-8dd0-e0bae5d6485b
Este documento es documento electrónico. Su autenticidad puede ser comprobada en la dirección
https://registro.emasa.es/CiudadaniaSeguimientoExpediente.aspx

SSS 2.1
CIRS

El nuevo tramo de red que proponen como reposición de la que se va a eliminar por afección de la nueva edificación, junto con el hidrante existente, entendemos que no es necesaria ya que se disponen de suficientes en la zona de influencia del hidrante que se va a retirar.

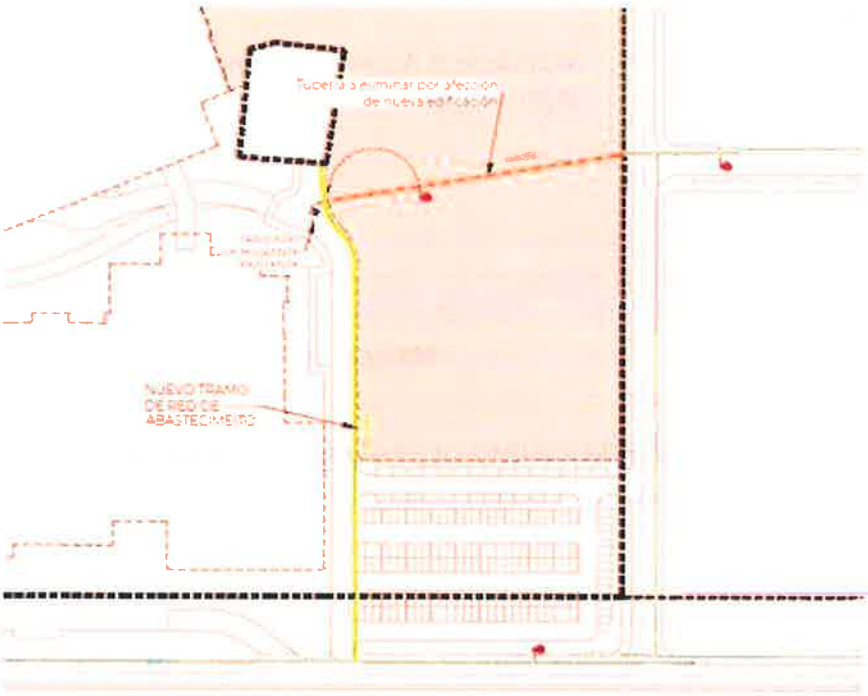

La nueva red de FD-100 que proponen para abastecer a las parcelas 13.1, 13.2, 14 y 15.2 no sería necesaria, ya que con las obras de urbanización de la Unidad de Ejecución UE-2 del Sector 3 del SUNP BM-3 se instalaron redes de distribución de agua potable, si bien, se deben revisar para ver si cumplen con los condicionantes técnicos exigidos por EMASA para su conexión y puesta en servicio. Adjuntamos plano con la red ejecutada.

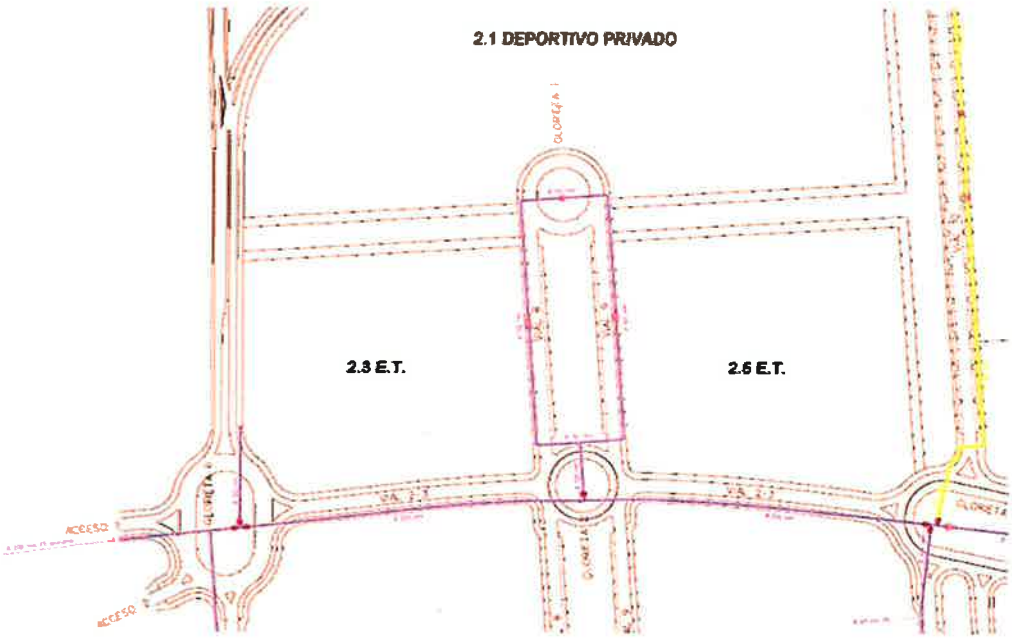

CSV: 07418d05-9813-4ed9-8dd0-e0bae5d6485b
Este documento es documento electrónico. Su autenticidad puede ser comprobada en la dirección https://registro.emasa.es/Ciudadania/SeguimientoExpediente.aspx

EMASA

REDES E INSTALACIONES DE AGUAS RESIDUALES

Nos parecen correctas las conexiones de las injerencias propuestas para las parcelas 5, 7.2, 15.1 y 15.2.

Las conexiones de las parcelas 13.1, 13.2, 13.3 y 14 se proyectan conectar a una red ejecutada pero no recepcionada. La red se ejecutó con las obras de urbanización de la Unidad de Ejecución UE-2 del Sector 3 del SUNP BM-3, pero en la actualidad no están recepcionadas por el Ayuntamiento. La conexión de estas injerencias será posible a ese colector, siempre y cuando esta infraestructura esté recepcionada por el Ayuntamiento. Si no lo estuviera, habría que proyectar un nuevo colector hasta conectar al actual en la Calle Clara Schumann.

El material de los colectores deberá ser PVC liso SN-8, y los pozos de registro serán prefabricados de PVC tipo "SANECOR". En cuanto a los marcos y las tapas, serán de fundición dúctil y cierre abisagrado En la tapa debe llevar las inscripciones de EMASA y SANEAMIENTO. Actualmente recomendamos las tapas REXESS de la empresa SAINT GOBAIN o las BRIO de empresa EJ para su uso en calzada.

Las conexiones de las injerencias de edificación se realizarán como norma general a pozo con junta elástica. En caso de conexión directa a tubería deberá utilizarse unión mecánica o clip con piezas de PVC.

Las arquetas de arranque de las injerencias deberán situarse próximas a las edificaciones previstas y en la medida de lo posible coordinarlas con los proyectos de edificación. Serán de PVC o PE sifónicos (con T y tapón), con al menos 40 cm de arenero bajo el sifón, para las fecales. El tamaño interior de la arqueta debería ser al menos de diámetro 600 mm. En el caso de las pluviales la arqueta puede ser de paso.

ARQUETA PREFABRICADA SIFÓNICA CON "T" Y TAPÓN

CSV: 07418d05-9813-4ed9-8dd0-e0bae5d6485b
Este documento es documento electrónico. Su autenticidad puede ser comprobada en la dirección https://registro.emasa.es/Ciudadania/SeguimientoExpediente.aspx

EMASA

ARQUETA PREFABRICADA DE PASO LIBRE

REDES E INSTALACIONES DE AGUAS PLUVIALES

Aún cuando las redes de drenaje de aguas pluviales no son competencia de EMASA, dada la similitud en cuanto a su funcionamiento con las redes de saneamiento y a la fuerte relación existente entre ambas infraestructuras, les trasladamos nuestra opinión técnica al respecto.

En cuanto a las conexiones previstas a la red de pluviales sucede lo mismo que en las residuales, las injerencias de las parcelas 13.1, 13.2, 13.3 Y 14, están previstas conectarlas a una red que no está recibida por el Ayuntamiento. Se ejecutaron con las obras de urbanización de la UE-2 del Sector del SUNP BM-3, pero están pendientes de recepción.

El material de los colectores deberá ser PVC liso SN-8. La ubicación de los imbornales en los viales deberá priorizar la instalación del tipo rejilla y buzón, en la línea de agua y junto a bordillo. Las arquetas deberán disponer de un arenero de no menos de 40 cm. de profundidad. Las rejillas deberán ser de 50x30 cm. C-250 mm.

El proyecto de urbanización contemplará técnicas de drenaje sostenible. Estas técnicas reducen la contaminación vertida, reducen los caudales de evacuación y potencia el flujo natural del agua pluvial hacia el subsuelo. Estas técnicas se deben emplear tanto para el drenaje de los viales y zonas verdes como para el drenaje de las parcelas privadas.

Atentamente.

07012545Y JUAN CARLOS TEJERO (R: A29185519)

Firmado digitalmente por 07012545Y JUAN CARLOS TEJERO (R: A29185519)
Fecha: 2021.11.16 13:35:42 +01'00'

Fdo.: Juan Carlos Tejero Moreno
Técnico Dpto. Ingeniería, Obras y Proyectos

CSV: 07418d05-9813-4ed9-8dd0-e0bae5d6485b
Este documento es documento electrónico. Su autenticidad puede ser comprobada en la dirección https://registro.emasa.es/CiudadaniaSeguimientoExpediente.aspx

S-2021-2036 16/11/2021 14:09:40

RED DE ABASTECIMIENTO

RED DE TRANSPORTE	VÁLVULA ABIERTA/ VÁLVULA CERRADA
RED ARTERIAL	VÁLVULA FRONTERA ABIERTA/ VÁLVULA FRONTERA CERRADA
RED PRINCIPAL	VÁLVULA DESAGÜE
RED DISTRIBUCIÓN	HIDRANTE - BOCA DE RIEGO
RED IMPULSIÓN	VENTOSA
RED FUERA DE SERVICIO PROVISIONAL	CAUDALÍMETRO
RED FUERA DE SERVICIO DEFINITIVO	CONTADOR
RED PROYECTADA	BOMBA
RED EN SERVICIO PROVISIONAL	VÁLVULA DE CONTROL AUTOMÁTICO
RED AJENA	PUNTO DE CONTROL
ACOMETIDA	FILTRO
DEPOSITO	VÁLVULA ANTIRRETORNO

EMASA

Empresa Municipal
Aguas de Málaga

ESCALA: 1/3.500	PLANO: RED DE ABASTECIMIENTO EXISTENTE AMPLIACIÓN DE PLAZA MAYOR (EXP. 2021/0081)	HOJA Nº: 1
FECHA: 05/11/2021		
OPERADOR GRÁFICO: JAIME JIMÉNEZ, INMACULADA		

Este documento es copia del original depositado en EMASA. Su almacenamiento y distribución por medios electrónicos está sometido a la legislación vigente en materia de propiedad intelectual.

S-2021-2036 16/11/2021 14:09:40

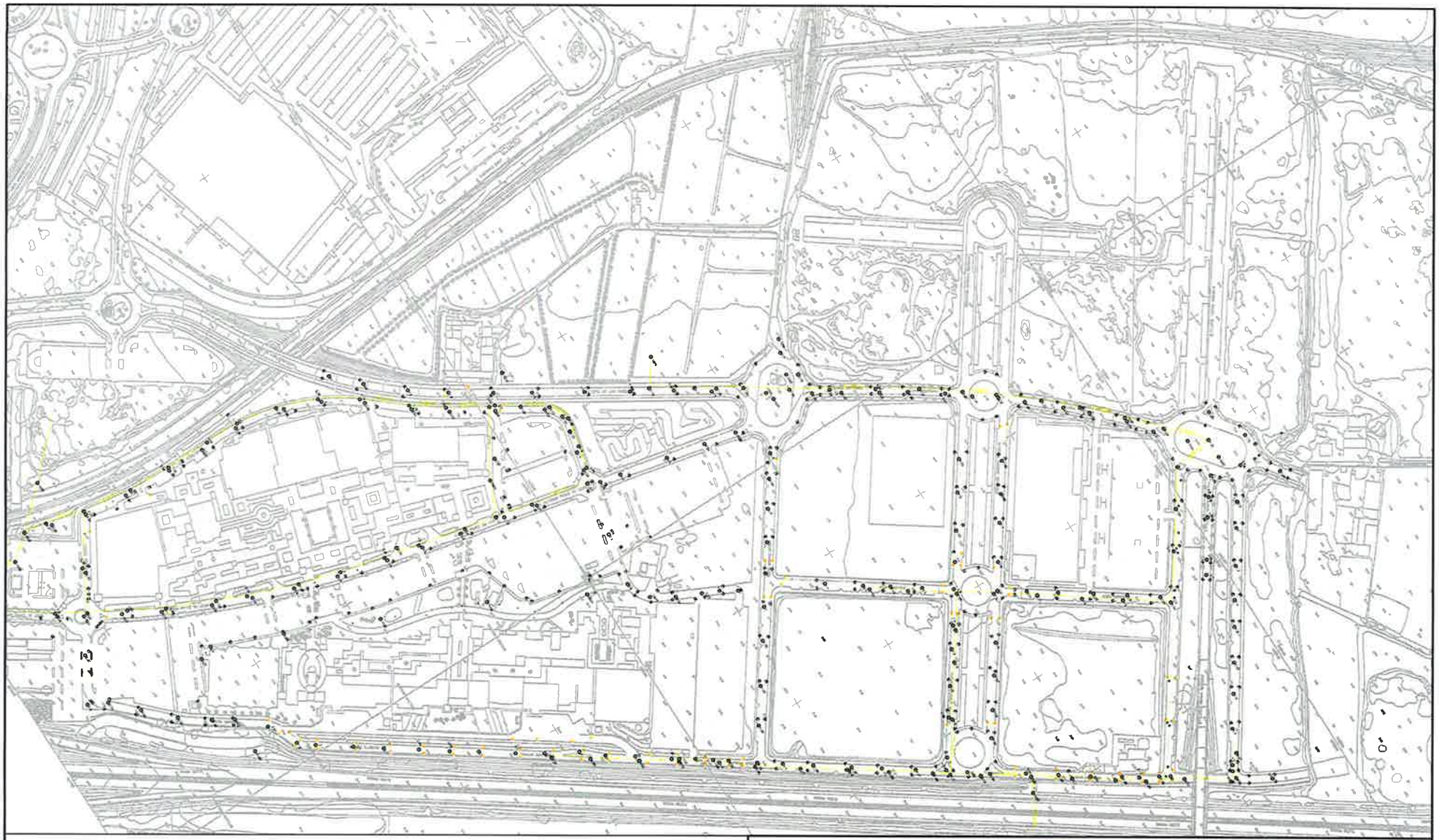

RED DE SANEAMIENTO

	RED UNITARIA		PUNTO DE VERTIDO
	RED FECALES		POZO CON REGISTRO
	RED PLUVIALES		UNION SIN REGISTRO
	CONDUCTO ALIVIADERO		PUNTO DE VERTIDO
	RED DE IMPULSION		BUZON
	INJERENCIA UNITARIA		REJILLA / REJILLA CON BUZÓN
	INJERENCIA FECALES		REJILLA TRANSVERSAL / REJILLA TRANSVERSAL CON BUZON
	INJERENCIA PLUVIALES		ARQUETA INJERENCIA CON REGISTRO
	ALIVIADERO		INICIO INJERENCIA SIN REGISTRO

EMASA

Empresa Municipal
Aguas de Málaga

ESCALA: 1/3.500	PLANO: RED DE SANEAMIENTO EXISTENTE AMPLIACIÓN DE PLAZA MAYOR (EXP. 2021/0081)	HOJA Nº: 1
FECHA: 05/11/2021		
OPERADOR GRÁFICO: JAIME JIMÉNEZ, INMACULADA		

EMASA

Empresa Municipal
Aguas de Málaga

AIEP
EJECUCIÓN DEL PLANEAMIENTO, S.L.

26 NOV. 2021

Registro de ENTRADA
Nº 3301

TELÉFONO DEL AGUA
900 777 420
24h • Llamada gratuita

za General Torrijos, 2
f. Hospital Noble. 29016 Málaga
ww.emasa.es